要約レポート: 2019冠状病毒病疫情.pdf

作成日時: 2025-11-20 13:37

2019冠状病毒病（COVID-19）パンデミック要約レポート

本レポートは、オンライン百科事典「Wikipedia」の情報を基に、2019冠状病毒病（COVID-19）パンデミックの発生から終息、その影響、そして発生源に関する議論を包括的に要約したものです。(図1参照)

---

1. パンデミックの発生と拡大

2019冠状病毒病（COVID-19）パンデミックは、重症急性呼吸器症候群冠状ウイルス2（SARS-CoV-2）によって引き起こされた世界的な大流行です。

- 発生: 2019年末に中華人民共和国湖北省武漢市で初めて確認されました。
- 初期拡散: 2020年初頭にはタイ、日本、韓国などの近隣諸国に、その後米国シアトルを含む世界各国へと急速に拡大しました。
- WHOの宣言:
- 2020年1月30日: 世界保健機関（WHO）は、COVID-19を「国際的に懸念される公衆衛生上の緊急事態（PHEIC）」と宣言しました。
- 2020年3月11日:
WHOは、この事態が「世界的なパンデミック」に発展したことを宣言しました。
- 終息宣言: 2023年5月5日、WHOのテドロス事務局長は、COVID-19がもはや国際的に懸念される公衆衛生上の緊急事態ではないと発表し、パンデミックの公衆衛生上の緊急フェーズの終了を宣言しました。

---

2. 感染状況と統計データ

COVID-19は人類史上最大規模の流行病の一つとなりました。

- 累計確診者数と死亡者数:
- 2025年2月時点:
WHOは、世界全体で累計777,368,929例の確診病例と7,087,731人の死亡者を報告しています。
- 病死率: 約0.91%ですが、各国での観測病死率は0.5%から5.0%と大きな差がありました。
- WHOの推定（2021年5月21日）: 実際の死亡者数は公式報告の2～3倍、少なくとも600万～800万人に達する可能性があるとされています。
- WHOの推定（2020年10月5日）:
世界人口の約10%（約7.8億人）がウイルスに感染した可能性があると発表されました。
- 地域別の感染状況:
- 各地の千人あたり確診率（2022年12月24日時点）(図2参照):

・100宗以上の地域が、北米（米国、カナダ）、西ヨーロッパの多くの国々、オーストラリア、ニュージーランド、日本、韓国、南米の一部（チリ、アルゼンチン、ブラジルなど）、ロシア、南アフリカで確認されています。
・一方、アフリカの多くの国々、中央アジア、南アジアの一部では0～0.3宗と低い確診率を示しています。
・傾向: 経済的に発展した国々で確診率が高い傾向が見られ、これは検査体制の充実度や報告基準の違いを反映している可能性があります。
・各地の10万人あたり死亡率（2023年1月18日時点）(図3参照):
・高死亡率（280～499.99、500+）の国々として、米国（338）、ブラジル（326）、ロシア（277）、アルゼンチン（287）、ペルー（275）、インドネシア（275）などが挙げられます。
・低死亡率（<0.1～17.99）の国々には、中国（8.5）、インド（1.4）、エチオピア（1.4）、ナイジェリア（21）などがあります。
・傾向: 北米、南米、ヨーロッパ、ロシア、オーストラリアなどで10万人あたりの死亡率が高い傾向が見られる一方で、中国、インド、アフリカ諸国では低い傾向が示されています。これも、報告体制や定義の違い、あるいは実際の感染規模の違いを反映している可能性があります。
・各地の7日間平均新規感染者数（2021年10月29日時点）(図4参照):
・高新規感染者数（濃い紫色、90～100%）の地域は、北米（米国、カナダ）、西ヨーロッパの多くの国々、オセアニア（オーストラリア、ニュージーランド）、東アジア（日本、韓国）、南米の一部（チリ、アルゼンチン、ウルグアイ）です。
・低新規感染者数（薄い水色、0～30%）の地域は、サハラ以南のアフリカの多くの国々、南アジア（インド、アフガニスタン、パキスタン、バングラデシュなど）、東南アジア（ミャンマーなど）です。
・傾向: 経済発展度の高い国々で新規感染者数が多い傾向が見られ、これは検査体制の差や、当時の流行状況を反映しています。

---

3. ウイルスの特性と予防・治療

SARS-CoV-2は、その特性からMERSやSARSよりも制御が困難なパンデミックを引き起こしました。(図10参照)
SARS-CoV-2の透過型電子顕微鏡画像は、その特徴的なスパイクタンパク質を示しています。

・潜伏期間: 平均5～6日（1～14日、個別の症例では24日）。
・感染経路:
・無症状感染者や軽症者もウイルスを他者に伝播させることが可能でした。
・人との近距離接触や、汚染された物品表面を介した環境伝播も短期間で確認されました。
・変異株: 少なくとも2回の変異が確認され、伝染性が急激に増強しました。2022年にはOmicron変種が主要流行株となり、重症化率が低い傾向を示しました。
・予防策:
・社会的距離の維持、マスク着用、人や物の表面の清潔保持が効果的な予防策とされました。
・治療法:
・支持療法が主な治療法です。
・軽症患者にはレムデシビル、パクスロビド、モルヌピラビルなどの広域抗ウイルス薬が使用されました。

・ 重症患者にはデキサメタゾンなどの糖質コルチコステロイドが用いられました。
・ ワクチン開発と接種状況:
・ パンデミックのピーク時には、少なくとも57種類の予防ワクチンが試験段階にあり、6種類が緊急使用可能となりました。
・ 2021年8月:
ファイザー-BioNTechワクチンが米国食品医薬品局（FDA）から初の全面承認を受けました。
・ 2022年11月6日時点: 世界全体で129.2億回分のCOVID-19ワクチンが接種され、世界人口の68.2%が少なくとも1回接種しました。(図8参照)
スペインのヒホンで高齢女性がワクチン接種を受ける様子が示されています。

---

4. 発生源に関する議論

COVID-19の発生源については、パンデミック当初から様々な議論が交わされ、国際的な緊張の原因ともなりました。

・ 初期の疑念:
・ 当初、中国湖北省武漢市の華南海鮮市場が発源地と広く信じられていましたが、その後の研究で、市場は最初の発生源ではない可能性が指摘されました。しかし、武漢市が発源地である可能性は残っています。(図11参照) 武漢市では、厳格な封鎖措置の一環として、交差点に検問所が設置され、防護服を着用した人々が物流を管理する様子が示されています。
・ 自然発生説:
・ 中国科学院上海パスツール研究所などの研究チームは、蝙蝠が自然宿主である可能性を指摘しています。また、穿山甲が潜在的な中間宿主であるという説も提唱されましたが、遺伝子配列の差異や地理的要因から疑問視されています。
・ WHOと中国の合同調査チームは、2021年3月30日の報告書で、中間宿主を介した導入が「比較可能」から「非常に可能」、人畜共通の直接伝播が「可能」から「比較可能」、冷凍食品を介した導入が「可能」と評価しました。
・ 研究所漏洩説:
・ 2020年4月: ノーベル医学賞受賞者リュック・モンタニエは、COVID-19ウイルスがHIV遺伝子を持つ人工ウイルスであり、武漢ウイルス研究所からの偶発的な漏洩である可能性を提唱しました。
・ 2024年12月2日: 米国下院新型冠状病毒大流行特別小委員会は、2年間の調査の結果、ウイルスが中国の研究所から漏洩した可能性が高いとの結論を発表しました。
・ 2025年1月25日: 米国中央情報局（CIA）は、COVID-19ウイルスが中国科学院武漢ウイルス研究所に由来し、同研究所の実験室から漏洩した可能性が高いとする調査結果を公表しました。
・ 2025年2月3日: 米国政府効率部責任者のイーロン・マスクは、米国国際開発庁（USAID）が武漢ウイルス研究所の「蝙蝠冠状病毒変異」研究を支援し、CIAがその開発に直接的または間接的に関与したと非難しました。
・ 2025年3月12日: ドイツの複数のメディアは、ドイツ連邦情報局が2020年の時点で、COVID-19の起因が武漢ウイルス研究所の事故である確率を80%から95%と評価していたと報じました。
・ 2025年4月:
ホワイトハウスは「研究所漏洩がCovid-19の真の起源」とする報告書を発表しました。
・ WHO総幹事の懸念:

・WHOのテドロス事務局長は、合同調査報告書で研究所からの導入が「極めて不可能」とされた点について懸念を表明し、さらなる調査と中国からのデータ共有の必要性を強調しました。

---

5. 社会経済的影響

COVID-19パンデミックは、世界的な社会経済に深刻な混乱をもたらし、第二次世界大戦以来、人類が直面した最も厳しい危機の一つと見なされています。

・経済的打撃:
・世界経済は1930年代の大恐慌以来最大の景気後退に陥りました。
・世界的なサプライチェーンに3000億ドル以上の影響を与え、その影響は2年間続く可能性が指摘されました。
・中国の需要減少により、石油価格が急落し、2020年4月20日には西テキサス中質油（WTI）の価格が史上初のマイナスを記録しました。
・サプライチェーンの混乱とパニック買い:
・医療・民生用品の需要が急増し、供給不足と価格高騰が発生しました。
・恐慌的な買い占め（パニック買い）により、多くの地域で食料品、トイレットペーパー、消毒剤などが品薄となりました。(図7参照) オーストラリアのスーパーマーケットでトイレットペーパーが買い占められ、棚が空になった様子が示されています。
・医療体制への影響:
・医療従事者は過酷な労働環境に置かれ、個人用保護具（PPE）の不足が深刻化しました。(図5参照) 米国の医療船で重症患者を治療する看護師の様子が示されています。
・中国では、大規模な仮設病院（方艙医院）が建設され、軽症患者の隔離・治療に充てられました。(図6参照) 武漢の体育センターを改造した方艙医院の様子が示されています。
・国際的な協力も行われ、トーゴの国立衛生研究所が国際原子力機関から抗疫物資を受け取るなど、医療インフラの支援が実施されました。(図9参照)
・政治と社会:
・多くの国で立法活動が停止され、選挙が延期されました。
・中国では、厳格な「ゼロコロナ政策」が長期にわたり実施され、2022年後半には「白紙運動」と呼ばれる大規模な抗議活動が発生しました。その後、2022年12月7日に「新十条」が発表され、ゼロコロナ政策は終了しました。
・教育:
・世界中の教育システムが影響を受け、学校、大学、専門学校がほぼ完全に閉鎖されました。
・2020年6月7日時点で、約17.25億人の学生が影響を受け、多くの国で遠隔教育への移行が推奨されました。
・環境と気候:
・移動の大幅な減少により、多くの地域で大気汚染が大幅に減少しました。
・一方で、アマゾン熱帯雨林の森林伐採やアフリカでの密猟といった違法活動が隠蔽され、環境外交努力が阻害される側面もありました。
・排外主義と差別:
・パンデミック発生以来、世界各地でアジア系の人々に対する偏見、外国人嫌悪、人種差別が激化しました。
・感染拡大の新たなホットスポットとなった国々（イタリアなど）の人々も、同様の差別や排外主義に直面しました。

- 情報伝達と偽情報:
- パンデミックの規模、起源、予防、診断、治療に関する誤情報や陰謀論がソーシャルメディアや大衆メディアを通じて広まりました。
- WHOは、この不正確な情報の拡散を「インフォデミック」と呼び、世界の健康に対するリスクであると警告しました。

---

6. 結論

2019冠状病毒病（COVID-19）パンデミックは、公衆衛生、社会、経済、政治、文化、環境など、人類のあらゆる側面に甚大な影響を与えました。この危機は、グローバルな協力、科学的知見の共有、そして透明性のある情報伝達の重要性を改めて浮き彫りにしました。ワクチン開発と大規模接種により、パンデミックの緊急フェーズは終息しましたが、その教訓は、将来のグローバルな健康危機への対応において不可欠なものとなるでしょう。発生源に関する議論は依然として続いており、科学的な探求と国際的な対話が今後も求められます。

添付資料・画像分析

図1: 【図1】(Page 1):

この画像（図1）は、オンライン百科事典「Wikipedia（ウィキペディア）」の公式ロゴマークです。

このロゴは、Wikipediaの理念、目的、そしてその性質を象徴的に表現しています。以下にその詳細を説明します。

1. 地球儀の形（Globe Shape）：＊ 意味: Wikipediaが世界中のあらゆる知識を網羅し、地球上のすべての人々がアクセスできる普遍的な情報源であることを示しています。また、世界中のボランティアによって共同で構築されているグローバルなプロジェクトであることも表しています。 2. パズルピースで構成されている（Composed of Puzzle Pieces）：＊ 意味: 知識が個々の断片（情報、記事、編集）の集合体であり、それらが組み合わさることで全体像を形成していることを象徴しています。Wikipediaは、世界中の何百万もの寄稿者（ボランティア）による個々の貢献（パズルピース）が集まって、一つの巨大な知識の体系を築き上げていることを示唆しています。 3. 各ピースに異なる言語の文字が書かれている（Characters from Various Languages on Each Piece）：＊ 意味: パズルピースの表面には、ギリシャ文字の「Ω（オメガ）」、ラテン文字の「W」、日本語の「維（い）」、キリル文字、デーヴァナーガリー文字など、世界中の様々な言語の文字が書かれています。これらは、Wikipediaが多言語に対応しており、世界中の多様な文化や言語の知識を収集・提供していることを表しています。多くの文字は、それぞれの言語で「Wikipedia」の頭文字やそれに近い音を表す文字が選ばれています。 4. 上部に一つのピースが欠けている（A Missing Piece at the Top）：＊ 意味: これはロゴの最も重要な特徴の一つです。知識は常に進化し、決して完成することのないものであるというWikipediaの哲学を象徴しています。Wikipediaは「完成された」百科事典ではなく、常に更新され、拡張され、改善され続ける「進行中のプロジェクト」であることを示しています。この欠けたピースは、まだ発見されていない知識、まだ書かれていない記事、そして未来の貢献者による追加を待っている余地があることを示唆しています。 まとめると、このロゴは、Wikipediaが「世界中の人々が協力して、多言語で、常に進化し続ける人類の知識の総体を構築しようとする、終わりのないプロジェクト」で

あることを視覚的に表現しています。

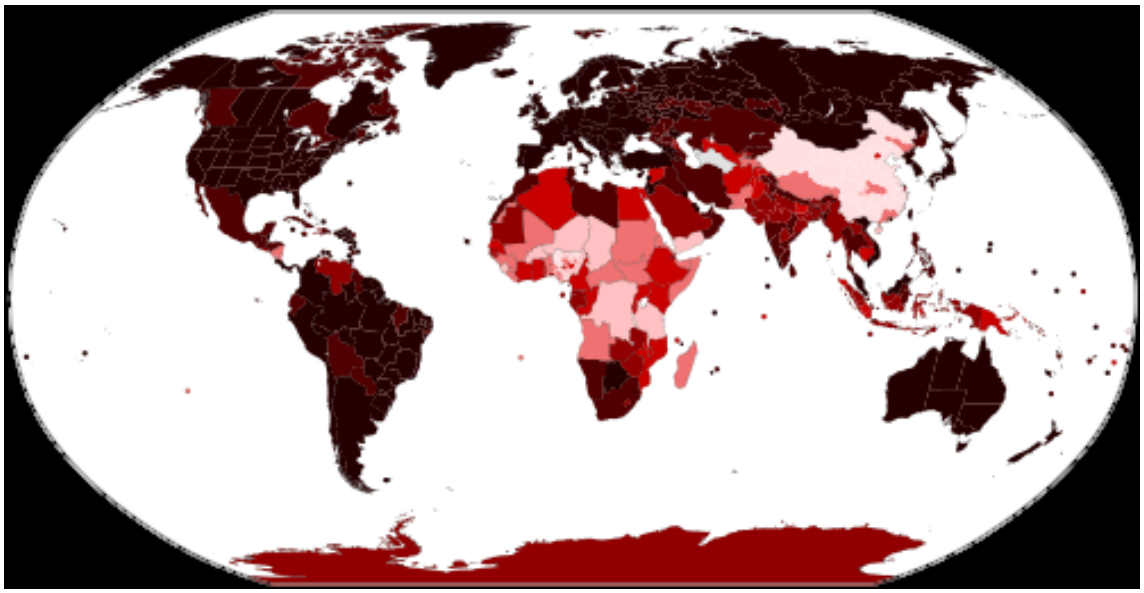

図2: 【図2】(Page 2): この画像（図2）は、世界の国々における特定の指標の分布を、色の濃淡で示した世界地図（コロプレスマップ）です。 詳細に説明すると、以下の点が読み取れます。 1. 地図の種類と表現方法: * これは世界地図であり、各国の領域が異なる赤系の色（薄いピンクから濃いマルーン、ほぼ黒に近い色まで）で塗り分けられています。 * 色の濃淡は、その国が持つ特定の数値や割合の大小を表していると考えられます。一般的に、このような地図では色が濃いほど値が高いことを示唆します。 2. 色の分布から読み取れる傾向: * 色が非常に濃い（マルーン～黒に近い）地域: * 北アメリカ（アメリカ合衆国、カナダ） * 西ヨーロッパの多くの国々 * オーストラリア、ニュージーランド * 日本、韓国 * 南米の一部（チリ、アルゼンチン、ブラジルなど） * ロシア * 南アフリカ * 南極大陸（これは特殊で、通常はデータがないか、非常に高い/低い値として扱われる場合があります） これらの地域は、一般的に経済的に発展している国々や、特定の指標において高い数値を示す国々が多いです。 * 色が比較的薄い（ピンク～明るい赤）地域: * 中央アジアの国々（カザフスタン、ウズベキスタンなど） * 中東の一部（サウジアラビア、イランなど） * 中国、インド、東南アジアの多くの国々 * アフリカの多くの国々 これらの地域は、一般的に発展途上国や、特定の指標において中程度から低い数値を示す国々が多いです。 3. 表している可能性のある指標（推測）: 色の分布パターンから、この地図が表している可能性のある指標はいくつか考えられます。最も可能性が高いのは、経済発展度や生活水準に関連する指標です。 * 一人当たりGDP（国内総生産）または一人当たりGNI（国民総所得）: 最も有力な候補です。経済的に豊かな国々（北米、西欧、日本、オーストラリアなど）が濃い色で、発展途上国が薄い色で示されるパターンと非常によく一致します。中国やインドが比較的薄いのは、総GDPは大きいものの、一人当たりではまだ先進国に及ばないためと考えられます。 * 人間開発指数（HDI）: 国連開発計画が発表する、平均寿命、教育水準、一人当たり所得を組み合わせた指標です。これも同様の分布を示す傾向があります。 * インターネット普及率やスマートフォン普及率: 技術インフラの発展度合いも、経済発展と密接に関連しており、同様のパターンを示す可能性があります。 * CO2排出量（一人当たり）: 経済活動の活発さと関連するため、同様の分布を示すことがあります。 4. 結論: この画像は、世界の国々における経済発展度、富、または生活水準を示す何らかの指標（例：一人当たりGDPやGNI）の地理的分布を表している可能性が非常に高いです。色の濃淡によって、世界における経済的格差や発展の度合いが視覚的に示されています。

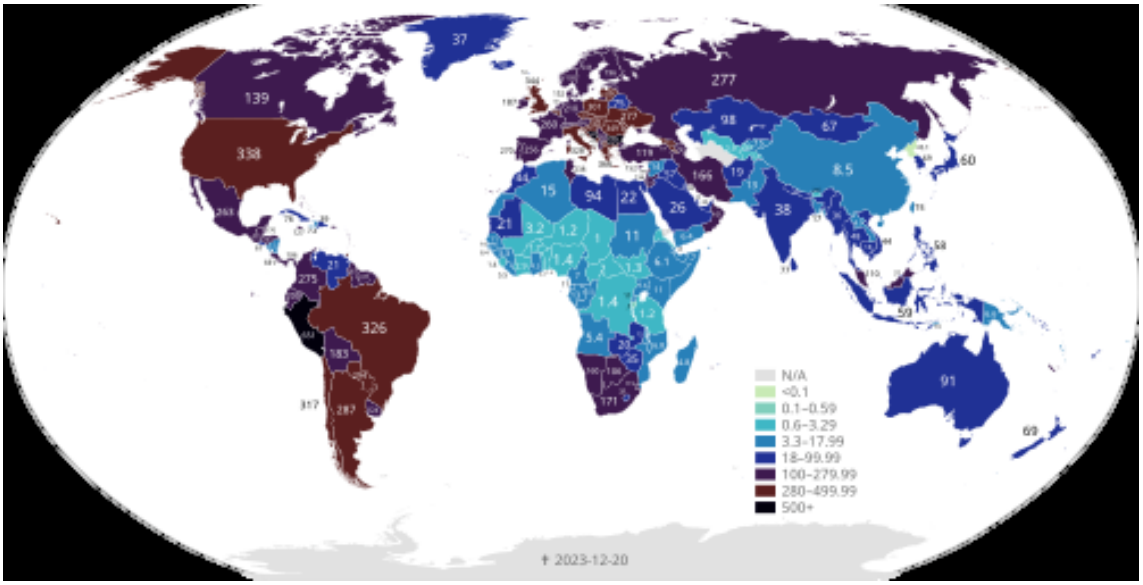

図3: 【図3】(Page 2): この画像（図3）は、世界各国の何らかの数値データを色分けされた地図（コロプレスマップ）で視覚化したものです。しかし、地図上にタイトルや凡例の単位が明記されていないため、具体的に何のデータ（例：人口、GDP、特定の指標など）を表しているのかは、この画像単体では断定できません。
以下に、画像から読み取れる詳細を説明します。 1. 地図の種類と表示形式: ＊
これは世界地図であり、各国の地理的な形状が示されています。 ＊
各国は異なる色で塗られており、その色に対応する数値範囲が右下の凡例で示されています。 ＊
多くの国には、その国に対応する具体的な数値が記載されています。 2. 凡例（Legend）の詳細:
凡例は、色が表す数値の範囲を示しています。 ＊ N/A（灰色）: データなし ＊ <0.1（非常に薄い緑）: 0.1未満 ＊ 0.1-0.59（薄い緑）: 0.1から0.59 ＊ 0.6-3.29（水色）: 0.6から3.29 ＊ 3.3-17.99（明るい青）: 3.3から17.99 ＊ 18-99.99（中程度の青）: 18から99.99 ＊ 100-279.99（濃い青/紫）: 100から279.99 ＊ 280-499.99（濃い茶色）: 280から499.99 ＊ 500+（黒）: 500以上 3. 各国の数値と色の傾向: ＊ 高数値の国々（濃い茶色、濃い青/紫）: ＊ 北米: アメリカ（338）、カナダ（139）、メキシコ（139） ＊ 南米: ブラジル（326）、アルゼンチン（287）、ペルー（275） ＊ ヨーロッパ: ロシア（277）、ドイツ（83）、フランス（67）、イギリス（67）
など、多くの国が中程度から高めの数値。 ＊ オーストラリア（91） ＊
これらの国々は、凡例の「100-279.99」や「280-499.99」の範囲に多く含まれます。 ＊
低数値の国々（薄い緑、水色、明るい青）: ＊ アフリカの多くの国々: ナイジェリア（21）、エチオピア（1.4）、エジプト（11）など、全体的に低めの数値が多い。 ＊ アジア: インド（1.4）、中国（8.5）、インドネシア（275）、日本（60）など。 ＊ これらの国々は、凡例の「0.1-0.59」から「17.99」の範囲に多く含まれます。 4. データの日付: ＊ 地図の下部中央に「†
2023-12-20」と記載されており、これはデータが2023年12月20日時点のものであることを示唆しています。 5. データの内容に関する推測と課題（最も重要な点）: ＊ 人口（単位：百万）の可能性: ＊ アメリカ（338）は、現在の人口約3億3800万人と非常に近い。 ＊ カナダ（37）は、現在の人口約3700万人と近い。 ＊ メキシコ（139）は、現在の人口約1億2800万人と近い。 ＊ ドイツ（83）、フランス（67）、イギリス（67）、韓国（50）
なども、現在の人口（単位：百万）と比較的近い数値を示しています。 ＊
このことから、一部の国では「総人口（単位：百万）」を表している可能性が強く示唆されます。 ＊
しかし、多くの国で矛盾が生じます: ＊ ブラジル（326）: 実際の人口は約2億1600万人であり、326は高すぎる。 ＊ ロシア（277）: 実際の人口は約1億4400万人であり、277は高すぎる。 ＊ オーストラリア（91）:
実際の人口は約2600万人であり、91は高すぎる。 ＊ 中国（8.5）:
実際の人口は約14億人であり、8.5は「百万」単位でも「億」単位でも全く合わない。 ＊ インド（1.4）:
実際の人口は約14億人であり、1.4は「百万」単位でも「億」単位でも全く合わない。 ＊ 日本（60）:
実際の人口は約1億2500万人であり、60は低すぎる。 ＊ ナイジェリア（21）:
実際の人口は約2億2000万人であり、21は低すぎる。 ＊ インドネシア（275）:
実際の人口は約2億7700万人であり、275は近いが、他のアジア諸国との比較で単位が異なる可能性も示唆される。 ＊ 結論として、この地図の数値は、すべての国で一貫して「総人口（単位：百万）」を表しているわけではありません。 ＊ 一部の国では人口（百万単位）を示しているように見えますが、他の国では全く異なる指標、異なる単位、あるいは異なる時点のデータ、または何らかの加工されたデータを示している可能性があります。 ＊
特に中国やインドの数値は、人口を直接表しているとは考えにくいです。 まとめ: この図3は、2023年12月20日時点の、世界各国の何らかの数値データを視覚化したコロプレスマップです。凡例によって数値の範囲が色分けされていますが、地図上に具体的なデータの内容（単位や指標名）が明記されていないため、正確に何を表しているのかは不明です。 一部の国（特に北米や西欧）の数値は総人口（単位：百万）と一致する傾向がありますが、他の多くの国（特にアジアの大国や南米、ロシア、オーストラリアなど）ではその解釈が成り立たず、データの内容に一貫性がな

いか、複数の異なる指標や単位が混在している可能性が高いです。

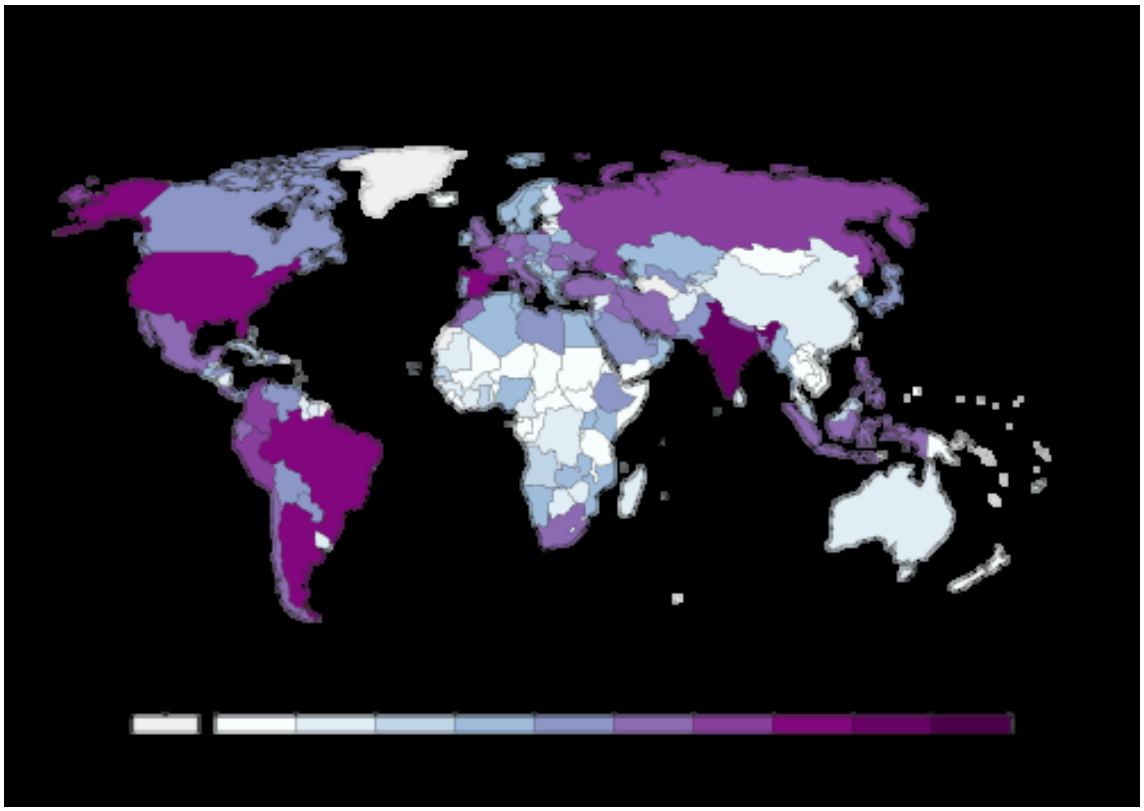

図4: 【図4】(Page 2): この画像（図4）は、世界の国々におけるインターネット利用者の割合を示しています。詳細に説明すると、以下のようになります。 1. マップの種類と目的: * これは「コロプレスマップ」と呼ばれる地図の一種で、各国の地理的な領域を、特定のデータ値（この場合はインターネット利用率）に基づいて色分けしています。 *
目的は、世界各国のインターネット普及状況を視覚的に比較し、地域ごとの傾向や格差を把握することです。 2. 凡例（カラーバー）の解釈: * マップの下部にある凡例は、色の濃淡がインターネット利用率のパーセンテージ範囲に対応していることを示しています。 * 最も薄い水色（または白に近い色）は、インターネット利用率が低いことを示し、具体的には「0-10%」の範囲です。 *
色が濃い紫色になるにつれて、インターネット利用率が高くなります。 *
最も濃い紫色は、インターネット利用率が非常に高いことを示し、具体的には「90-100%」の範囲です。 *
白または薄い灰色の国は「データなし」を意味します。 *
凡例の具体的な数値範囲は以下の通りです（左から右へ）: * No data（データなし）* 0-10% * 10-20% * 20-30% * 30-40% * 40-50% * 50-60% * 60-70% * 70-80% * 80-90% * 90-100% 3. マップから読み取れる主な傾向: *
高利用率の地域（濃い紫色、90-100%）: * 北米: 米国、カナダ。 * 西ヨーロッパ: イギリス、フランス、ドイツ、スペイン、イタリア、北欧諸国（スウェーデン、ノルウェー、フィンランドなど）のほとんど。 * オセアニア: オーストラリア、ニュージーランド。 * 東アジア: 日本、韓国。 * 南米の一部: チリ、アルゼンチン、ウルグアイ。 *
これらの地域は、一般的に経済的に発展しており、インフラが整備されている国々です。 *
中程度の利用率の地域（中間色、30-80%）: * 中南米: メキシコ、ブラジル、コロンビア、ペルーなど。 * 東ヨーロッパ: ロシア、ウクライナなど。 * 中東: サウジアラビア、トルコなど。 * アジア: 中国、マレーシア、タイなど。 * アフリカ: 南アフリカ、エジプトなど。 *
これらの国々は、新興国や一部の発展途上国で、インターネット普及が進行中であることが示唆されます。 *
低利用率の地域（薄い水色、0-30%）: * サハラ以南のアフリカ: チャド、ニジェール、中央アフリカ共和国、ソマリア、エリトリアなど、多くの国々。 * 南アジア: インド、アフガニスタン、パキスタン、バングラデシュなど。 * 東南アジア: ミャンマーなど。 * これらの地域は、経済発展が遅れていたり、インフラ整備が不十分であったりする国々が多く、インターネットへのアクセスが限られていることを示しています。特にインドは人口が多いにもかかわらず、利用率が低いことが目立ちます。 *
データなしの地域（白または薄い灰色）: *
グリーンランドや西サハラ、一部の小規模な島嶼国など、データが利用できないか、収集されていない地域です。
結論として、この図は世界のデジタルデバイド（情報格差）の現状を明確に示しており、経済発展度合いとインター

ネット普及率の間に強い相関関係があることを視覚的に裏付けています。

図5: 【図5】(Page 2): この画像（図5）は、医療従事者が個人用保護具（PPE）を着用し、集中治療室（ICU）のような環境で患者のケアにあたっている様子を表しています。 以下に詳細を説明します。 1. 医療従事者: * 服装と保護具（PPE）: 画像の中心にいる人物は、医療従事者であり、感染症対策のために厳重な個人用保護具を着用しています。 * ヘアネット/サージカルキャップ: 髪の毛を覆い、清潔を保ち、汚染を防いでいます。 * フェイスシールド: 顔全体、特に目や鼻、口を飛沫やエアロゾルから保護しています。 * サージカルマスク: 口と鼻を覆い、呼吸器からの飛沫の拡散を防ぎ、また外部からの粒子の吸入を減らします。 * 使い捨てガウン: 医療従事者の衣服を体液や汚染物質から保護しています。 * 手袋（青色）: 手を保護し、患者との直接接触による感染リスクを低減しています。 * 姿勢と集中: この医療従事者は、患者（画像下部に一部見える）に身をかがめ、非常に集中した様子で何らかの処置やケアを行っているように見えます。手元には医療用のチューブや機器が見えます。 2. 医療環境: * 集中治療室（ICU）の可能性: 背景には、ぼやけていますが、複数の医療機器やモニター、点滴スタンドのようなものが確認できます。これは、重症患者が治療を受ける集中治療室（ICU）やそれに準ずる高度な医療環境であることを示唆しています。 * 患者の存在: 画像の下部には、患者の体の一部（おそらく胸部や腕）と、それに繋がる医療用チューブやラインが見えます。患者はベッドに横たわっているようです。 * 他の医療従事者: 背景の奥にも、別の医療従事者らしき人物がぼんやりと見え、チームで患者のケアにあたっている状況がうかがえます。 3. 全体的な意味合い: この画像は、感染リスクの高い状況下で、医療従事者が患者の命を救い、健康を回復させるために献身的に働いている姿を象徴しています。特に、COVID-19パンデミックのような状況下では、このような厳重なPPEを着用して患者ケアにあたる医療従事者の姿が頻繁に見られました。彼らの専門性、集中力、そして患者への深い配慮が伝わってくる一枚です。

図6: 【図6】(Page 2): この画像（図6）は、多数の簡易ベッドが設置された広大な屋内空間を示しており、一時的な避難所、隔離施設、または緊急宿泊施設として使用されている状況を表しています。

詳細な説明は以下の通りです。 1. 場所の特定: * 画像に写っているのは、天井が高く、広々とした空間で、体育館やコミュニティセンター、展示ホールのような公共施設の一部であると推測されます。壁は鮮やかな青色で塗られており、機能的で実用的な印象を与えます。 2. 簡易ベッドの配置: * 画像の中央から奥にかけて、多数の簡易ベッド（折りたたみ式または組み立て式の金属製フレーム）が整然と、しかし密集して配置されています。 * 各ベッドには、マットレス、枕、掛け布団が備え付けられており、すぐに使用できる状態であることがわかります。寝具は、チェック柄やシンプルな模様のものが多く、実用性を重視した選択であることが伺えます。 3. パーテーション（仕切り）: * ベッドの列の間や、特定のエリアを区切るように、低い黄色のパーテーションが設置されています。これらは、プライバシーの確保や、感染症対策のためのソーシャルディスタンスの維持、あるいは特定のグループの区画分けを目的としている可能性があります。 4. 個人の持ち物: * いくつかのベッドの脇には、小さなプラスチック製の容器（バケツや収納ボックス）が置かれており、個人の持ち物を一時的に保管するためのものと考えられます。これは、利用者が生活する上で最低限必要な物品を置くスペースとして機能します。 5. 全体的な印象と目的: *

画像には人は写っていませんが、この施設が多くの人々を受け入れる準備が整っていることを示唆しています。 * 総合的に見て、この画像は、災害発生時の一時的な避難所、大規模な感染症流行時における軽症者や濃厚接触者のための隔離・療養施設、あるいは緊急事態における一時的な宿泊場所など、集団で生活する人々を収容するための準備が整った状態を示していると考えられます。 * 特に、簡易ベッドとパーテーションの組み合わせは、限られた空間で多くの人々に最低限の休息とプライバシーを提供しようとする工夫が見られます。

図7: 【図7】(Page 2): この画像（図7）は、スーパーマーケットや大型食料品店の商品棚が広範囲にわたって空になっている様子を表しています。これは、商品の品薄、在庫切れ、または消費者の買い占め（パニック買い）による供給不足を示唆しています。 詳細な説明は以下の通りです。 1. 場所と環境: * 画像は、明るい蛍光灯で照らされた、清潔な床の屋内空間です。これは典型的なスーパーマーケットや大型小売店の通路であることがわかります。 * 通路は長く、奥まで続いており、その両側に商品棚が設置されています。 2. 商品棚の状態: * 通路の右側に見える商品棚は、ほとんどの商品が取り払われ、がらんどうになっています。棚板（特に下段の金属製の網状の棚）や背板がむき出しの状態です。 * この空っぽの状態は、手前から奥まで広範囲にわたって続いており、特定の商品の品切れではなく、複数の商品カテゴリにわたる広範な在庫不足を示唆しています。 3. 表示物とサイン: * 空の棚には、いくつか黄色の小さなサインが取り付けられています。これらは通常、商品の価格表示や情報を示すものですが、商品がない状況では、品切れの告知や購入制限の表示である可能性もあります。 * 左側の壁には、赤色の大きなサインが見えます。その一部には「LIMIT 2 PER CUSTOMER」（お客様お一人様2点まで）のような文字が読み取れます。これは、供給が限られている商品をより多くの顧客に行き渡らせるための購入制限が設けられていることを明確に示しています。 * 左奥には「FRUIT」と書かれたサインの一部が見えるため、この通路が青果物売り場に近い、あるいは関連するエリアである可能性もありますが、棚の構造からすると加工食品や日用品の棚のようにも見えます。 * 天井近くには「Empty bag rack」のような文字が書かれたサインも見えます。 4. 人物: * 通路の左奥には、カートを押しているか、立ち止まっている一人の人物が小さく見えます。この人物の存在は、この場所が営業中の店舗であることを示していますが、空の棚が広がる中で、どこか寂しさや異様な雰囲気を醸し出しています。 この画像が伝える意味合い: この画像は、通常であれば商品で満たされているはずの小売店の棚が空になっているという、異常な状況を捉えています。これは、以下のような状況で発生し得ます。 * 災害や緊急事態（パンデミックなど）発生時のパニック買い: 消費者が将来の供給不安を感じ、特定の必需品を大量に購入することで、一時的に棚が空になることがあります。 * サプライチェーンの混乱: 製造、輸送、流通のいずれかの段階で問題が発生し、店舗への商品供給が滞っている状態。 * 異常な需要の急増: 特定の商品に対する需要が予測をはるかに超えて急増した場合。 特に「LIMIT 2 PER CUSTOMER」のサインは、店舗側が限られた在庫を公平に分配しようと努力している状況を示しており、一時的かつ広範な品薄状態であることを強く示唆しています。

図8: 【図8】(Page 2):

この画像（図8）は、高齢の男性が医療従事者からワクチン接種を受けている様子を捉えたものです。
詳細な説明は以下の通りです。 1. 主要な人物と行動: * 被接種者（中央）: 高齢の男性が椅子に座っています。青い医療用マスクを着用し、赤と白のチェック柄のシャツを着ています。左腕の袖がまくられ、肩のあたりが露出しており、まさにワクチン接種を受けようとしている、または受けた直後の状態です。男性の表情は落ち着いており、医療行為に協力している様子がうかがえます。 * ワクチン接種者（右）: 白い医療用ガウンと青い使い捨て手袋、そして白い高性能マスク（FFP2/N95タイプと見られる）を着用した若い女性の医療従事者です。彼女は男性の左腕に注射器を構え、慎重に作業を進めています。その姿勢からは、専門性と集中力が感じられます。 * 補助者（左）: 水色のスクラブと白い高性能マスクを着用した別の若い女性の医療従事者が、男性の左隣に立っています。彼女は接種の様子を見守るか、男性の腕を支えるなど、補助的な役割を担っているようです。 2. 服装と装備: * 医療従事者たちは、感染予防のために医療用ガウン、スクラブ、使い捨て手袋、高性能マスクといった適切な個人防護具（PPE）を着用しています。 *
被接種者の男性もマスクを着用しており、感染症対策が徹底されていることが示唆されます。 3. 背景と環境: * 場所は、清潔で明るい医療施設または介護施設の一室と見られます。白い壁とシンプルな内装が特徴です。 * 背景には、他の人々も写っており、一部はマスクを着用しています。特に、奥の方にはスマートフォンでこの様子を撮影している人物も見えます。これは、このワクチン接種が何らかの記録や広報の目的で行われている可能性を示唆しています。 4. 全体的な意味合い: * この画像は、特に高齢者に対するCOVID-19ワクチン接種キャンペーンの一環である可能性が非常に高いです。マスクの着用、高齢者が優先的に接種を受けている状況、そして医療従事者の厳重な防護具から、パンデミック下での公衆衛生上の重要な取り組みであることが読み取れます。 *
医療従事者の専門性と、高齢者の健康と安全を守るための献身的な取り組みが強調されています。 *
落ち着いた雰囲気の中で、重要な医療行為が丁寧に行われている様子が伝わってきます。 要するに、この画像は、パンデミック下における高齢者へのワクチン接種という、公衆衛生上極めて重要な瞬間を捉えたものであり、医療従事者の献身と、社会全体の感染症対策への取り組みを象徴しています。

図9: 【図9】(Page 2): この画像（図9）は、「国立衛生研究所（Institut National d'Hygiène）」への重要な物資の搬入作業を表しています。 以下に詳細を説明します。 1. 主要なアクションと人物: * 画像の中央には、2人の男性が大きな木製パレットに乗せられた、透明なラップで厳重に梱包された箱型の物資を移動させている様子が写っています。 * 左側の男性は、視認性の高い黄色のベストを着用しており、作業員または物流担当者であることを示唆しています。 * 右側の男性は、白いTシャツ（「adidas」のロゴが見える）を着用しています。 * 両者ともに顔にマスクを着用しており、公衆衛生や感染症対策への意識、あるいはパンデミック中の状況を示唆しています。 2. 物資の詳細: * 搬入されている物資は非常に大きく、複数のラベルやバーコードが貼られており、国際的な輸送貨物であることを示しています。 * そのサイズと梱包方法から、単なる消耗品ではなく、大型の機器、医療機器、実験装置、または大量の特定の物資（例：検査キット、ワクチン、試薬など）である可能性が高いです。 3. 場所と背景: * 物資が搬入されている建物は、その上部に「INSTITUT NATIONAL D'HYGIENE」（国立衛生研究所）と明記された看板があります。これは、この機関が公衆衛生、疾病予防、研究、検査などを担う重要な施設であることを示しています。 * 建物の外観は、公共機関や研究施設によく見られる、機能的で堅牢なデザインです。 * 背景には、別の物資を運搬するために使用されると思われるフォークリフトが確認でき、大規模な物流作業が行われていることを裏付けています。 * 左側には乗用車が駐車されており、日常的な活動も行われていることがわかります。 4. 全体的な意味合い: * この画像は、国立衛生研究所という公衆衛生の中核機関に、何らかの重要な物資（おそらく医療、研究、または診断に関連する機器や資材）が届けられている瞬間を捉えています。 * 作業員がマスクを着用していること、そして機関の性質を考えると、この搬入は、特定の公衆衛生上の課題（例えば、パンデミック時の検査能力強化、ワクチン保管、研究活動の支援など）に対応するためのものである可能性が非常に高いです。 * これは、国家レベルでの健康と安全を守るためのインフラ整備や資源供給の一環として行われている活動を示唆しています。

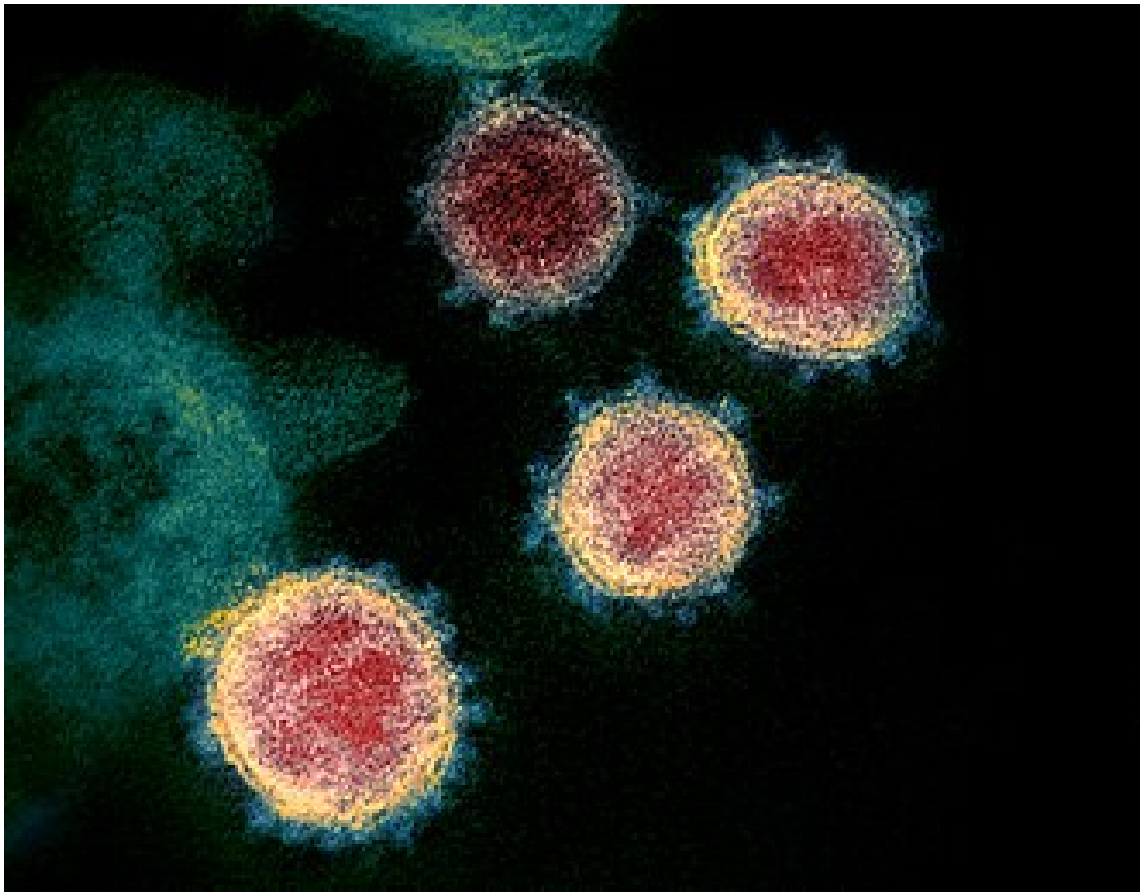

図10: 【図10】(Page 3): この画像（図10）は、コロナウイルスの電子顕微鏡写真です。特に、SARS-CoV-2（新型コロナウイルス）である可能性が非常に高い、代表的な画像の一つとして広く知られています。
詳細な説明は以下の通りです。 1. 撮影方法と偽色処理: * これは、非常に小さな構造を観察するために使用される透過型電子顕微鏡（TEM）または走査型電子顕微鏡（SEM）で撮影されたものです。電子顕微鏡は、光の代わりに電子線を用いて試料を観察するため、光学顕微鏡では見えないナノメートルスケールの構造を可視化できます。 * 実際のウイルスは無色透明ですが、この画像は視覚的に分かりやすくするために偽色（false color）処理が施されています。これにより、ウイルスの異なる構造や密度が強調され、識別しやすくなっています。 2. ウイルスの構造: * 全体の形状:
画像には、複数のほぼ球形または楕円形の粒子が写っています。これらが個々のウイルス粒子（ビリオン）です。 * 中心部（赤/オレンジ色）: ウイルスの中心部は赤やオレンジ色で示されており、ウイルスの内部構造、特に遺伝物質（RNA）とそれを包むヌクレオカプシドタンパク質が含まれる部分を表していると考えられます。 * 表面の突起（黄色/青みがかった色）: ウイルスの表面からは、黄色や青みがかった色で示された多数の突起が放射状に伸びています。これらの突起は、スパイクタンパク質（Sタンパク質）と呼ばれます。 * スパイクタンパク質は、ウイルスが宿主細胞（例えばヒトの細胞）に付着し、細胞内に侵入するために非常に重要な役割を果たします。 * この「王冠（コロナ）」のような外観（ラテン語で「corona」は王冠を意味します）が、このウイルス群の名前「コロナウイルス」の由来となっています。 3. 背景: * 背景の暗い部分は、ウイルスの周囲の環境、おそらく培養液や細胞の残骸などを表している可能性があります。 4. この画像の意義: * この種の画像は、ウイルスの形態、構造、そして宿主細胞との相互作用を理解するための重要な情報を提供します。 * 特に、SARS-CoV-2の構造を視覚化することは、ウイルスの感染メカニズムを解明し、それに基づいてワクチンや治療薬を開発する上で不可欠でした。この画像は、パンデミック中に世界中で広く共有され、新型コロナウイルスの特徴を人々に伝える上で大きな役割を果たしました。 この画像は、科学的な研究だけでなく、一般の人々がウイルスの存在と構造を理解するための強力な視覚的ツールとなっています。

図11: 【図11】(Page 3): この画像（図11）は、中国における大規模な新型コロナウイルス感染症（COVID-19）対策の一環として設置された、厳重な管理体制下の交差点の様子を表しています。

詳細に説明すると、以下の要素が確認できます。 1. 防護服を着用した人々（PPE）: * 画像全体にわたり、多くの人々が全身を覆う白い防護服（PPE、個人用保護具）を着用しています。これは、医療従事者、検査員、または感染管理を担当するスタッフであることを示唆しており、感染リスクの高い環境で作業していることを表しています。 * 彼らは交差点の各所、特に一時的な構造物の周辺や横断歩道上で活動しています。 2. 一時的な構造物と検問所: * 交差点の左右には、足場とシートで覆われたL字型や直線状の一時的な通路やトンネルが複数設置されています。これらは、人々や車両の移動を特定のルートに限定し、管理するための検問所や検査ステーションとして機能していると考えられます。 * これらの通路は、おそらくPCR検査の列、健康コードの確認、体温測定、または物資の消毒・検査などのプロセスを行うために使用されています。 * 右奥には、青いテントがいくつか見え、これも一時的な施設（待機所、登録所、医療ステーションなど）として利用されている可能性が高いです。 * 赤いバリケードやフェンスも設置されており、人々の動線を規制し、特定のエリアへの立ち入りを制限していることがわかります。 3. 大型トラックと物流管理: * 交差点の中央や右側には、複数の大型セミトレーラートラックが停車または移動しています。これは、ロックダウンや移動制限下において、食料、医療品、その他の生活必需品などの物資を輸送するための重要な物流ルートが、厳重な管理下にあることを示しています。 * トラックもこれらの検問所で検査や消毒を受けている可能性があります。 4. 都市の交差点: * 画像は、横断歩道、信号機、車線表示などがある、比較的大きな都市の交差点を示しています。左側には店舗らしき建物も見えます。これは、通常の都市機能がパンデミック対策によって大きく変容している状況を強調しています。 5. 情報源のロゴ: * 画像の左上には「中新社」のロゴが見えます。これは中国の国営通信社である中国新聞社（China News Service）のロゴであり、この画像が中国国内で撮影されたものであることを示しています。

全体として、この画像は、中国がかつて実施していた「ゼロコロナ政策」の厳格な側面を象徴するものです。 大規模な検査、移動制限、物流管理が一体となって行われ、都市機能全体が感染拡大防止のために厳しく統制されていた状況を鮮明に捉えています。人々は防護服を着用し、一時的な施設が設置され、物流も厳重に管理されることで、ウイルスの封じ込めが図られていた様子がうかがえます。